INCIDENTES DE TRÂNSITO – MARÇO DE 2026

No mês de março de 2026 foram registradas um total de 1.580 solicitações de atendimento devido a incidentes de trânsito. Em decorrência desses incidentes, foram atendidos um total de 1.953 pacientes.

O tipo de incidente mais frequente corresponde às colisões carro – moto (25,04%), seguido por quedas de moto (11,26%) e colisões carro – carro (9,01%). A quarta posição corresponde aos atropelamentos (8,81%). (Figura 1)

F 1

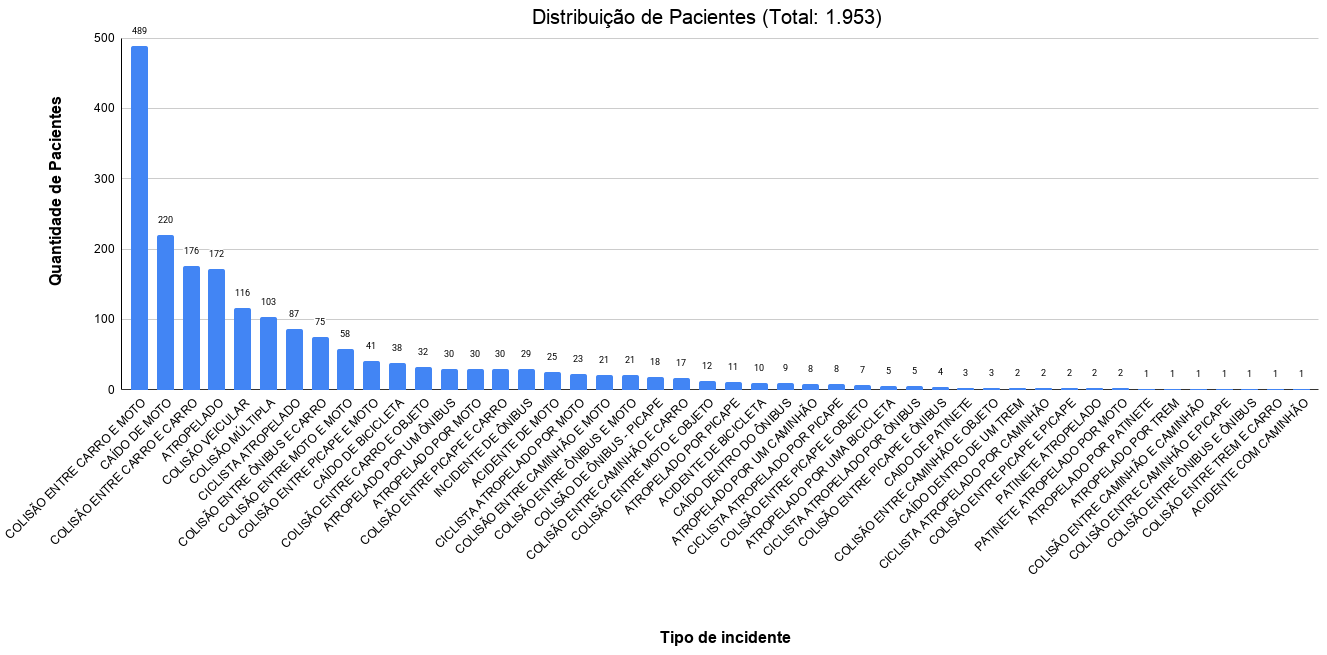

Do total de incidentes registrados, aqueles que envolveram motocicletas correspondem a 960 casos (42,8%), os que envolveram automóveis, 897 casos (40,0%), e os atropelamentos representam 387 casos (17,2%). (Figura 2)

F 2

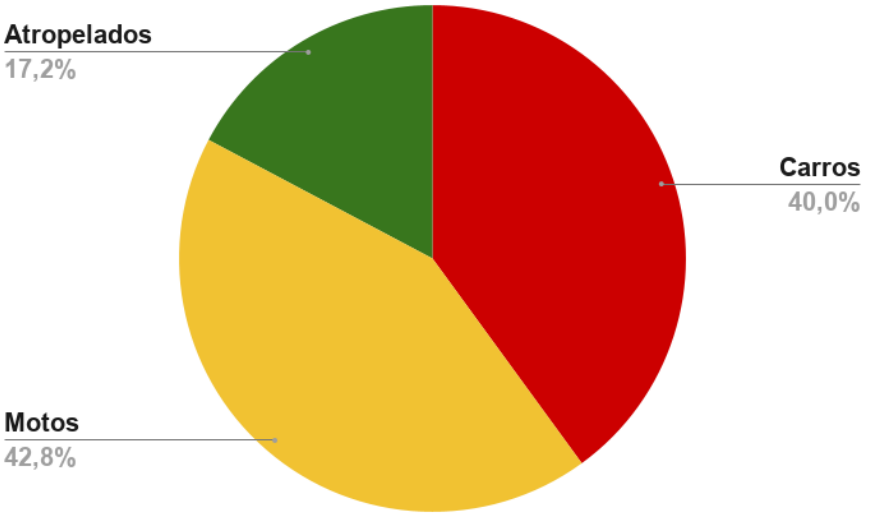

FREQUÊNCIA DE INCIDENTES DE ACORDO COM DIA-HORA

A maior ocorrência média de incidentes de trânsito foi observada às sextas-feiras, entre 20h e 22h. A maior quantidade de incidentes nas sextas-feiras nessa faixa horária pode estar relacionada a características próprias da dinâmica populacional durante o mês de março.

Esses dados representam médias calculadas a partir dos dados mensais, considerando as variáveis dia da semana, hora do dia e número de incidentes. (Figura 3)

F 3

Grade de Calor

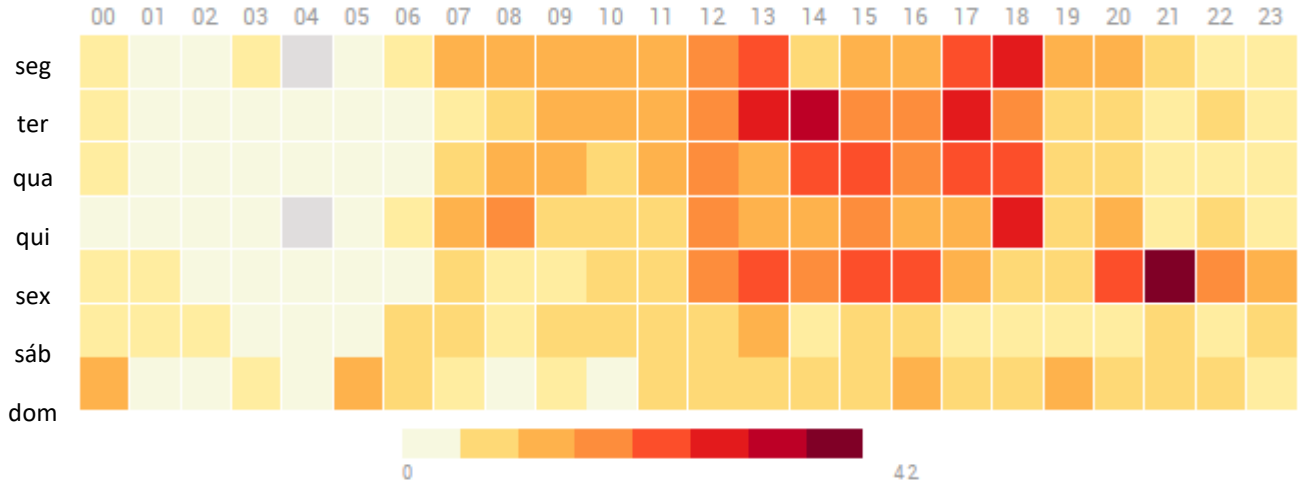

- Minimo 0. Dia: Seg. Hora: 04.
- Máximo 42. Dia: Sex. Hora: 21.

MAPA DE INCIDENTES

A maior incidência de atendimentos foi observada nas seguintes comunas.

- Comuna 1 (Retiro, Constitución, Monserrat, San Nicolas, Puerto Madero);
- Comuna 4 (La Boca, Barracas, Parque Patricios e Nueva Pompeya);
- Comuna 14 (Palermo);
- Comuna 3 (Balvanera, San Cristóbal);
- Comuna 9 (Liniers, Mataderos, Parque Avellaneda).

MAPA INTERATIVO

Este mapa interativo representa os incidentes de trânsito ocorridos no mês de março. Foi elaborado a partir de dados de geolocalização correspondentes a incidentes viários obtidos do SISeP - Sistema Integral de Segurança Pública (Sistema Integral de Segurança Pública, em Português), compreendidos entre 1º e 31 de março de 2026.

Para acessar o mapa interativo (Figura 4), clique no seguinte link:
https://goo.su/OcoOw1B

F 4

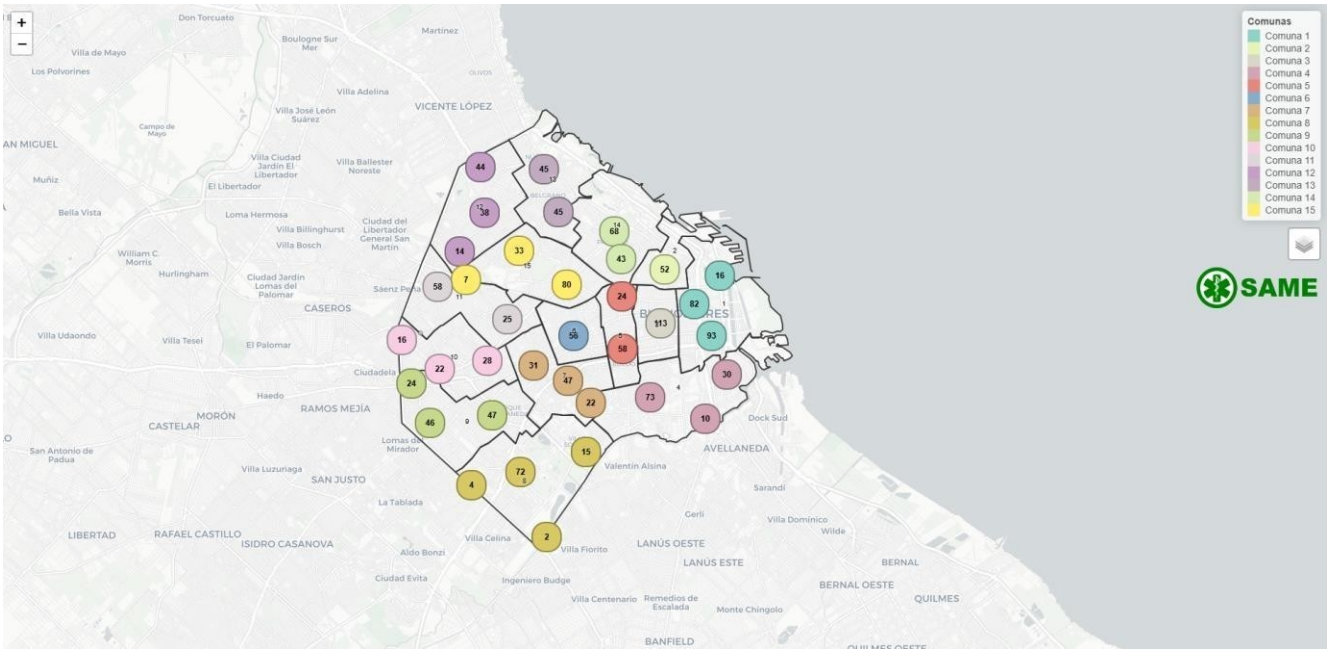

Instruções de uso

Ao abrir o link, será visualizado um mapa da Cidade Autônoma de Buenos Aires dividido por comunas. Dentro de cada uma delas, agrupam-se círculos que contêm um número, o qual indica a quantidade de incidentes viários ocorridos naquele raio durante o período de 2026. As cores dos círculos variam de acordo com a comuna correspondente.

Por meio dos botões “+” e “–”, localizados no canto superior esquerdo, é possível aproximar ou afastar o mapa (zoom). À medida que o nível de zoom é aumentado, a informação é desagregada em raios menores, permitindo visualizar os incidentes até o nível de cruzamentos de ruas específicas. (Figura 5)

F 5

No canto superior direito encontra-se a referência colorimétrica dos incidentes segundo a comuna (quadro amarelo) e, abaixo desta, o ícone correspondente às camadas do mapa (quadro azul). Ao posicionar o cursor sobre esse ícone, será exibida uma lista das camadas disponíveis. As camadas visíveis no mapa são aquelas que apresentam a caixa marcada com um tique azul. Para ocultar comunas ou linhas divisórias, deve-se desmarcar a caixa correspondente clicando no quadrado localizado à esquerda da opção que se deseja ocultar.

Ao clicar sobre os círculos coloridos, o mapa realizará uma aproximação automática ao raio dos incidentes selecionados. Esse procedimento pode ser repetido sucessivamente, permitindo um maior nível de detalhamento até alcançar a visualização dos incidentes conforme o traçado de ruas específicas e abrir as especificações do incidente, exibindo o tipo de incidente, o transporte/remoção e as coordenadas. (Figura 6)

F 6

DADOS PARA A REPRODUTIBILIDADE DESTE RELATÓRIO

Período: 01/03/2026 às 00:00h até 31/03/2026 às 24:00h. Foram utilizados os filtros Colisão Veicular, Queda de Veículo e Atropelamento (Choque Vehicular, Caído Vehículo y Atropellado). Todos os eventos associados foram excluídos. Não foram adicionados outros filtros. Os dados utilizados foram obtidos do SISeP - Sistema Integral de Segurança Pública (Sistema Integral de Segurança Pública, em Português).

Para citar o presente relatório, solicitamos utilizar o seguinte formato: Relatório mensal de incidentes de trânsito 2026. Sistema de Atendimento Médico de Emergências, Governo da Cidade Autônoma de Buenos Aires. SAME – GCBA. ECUES.